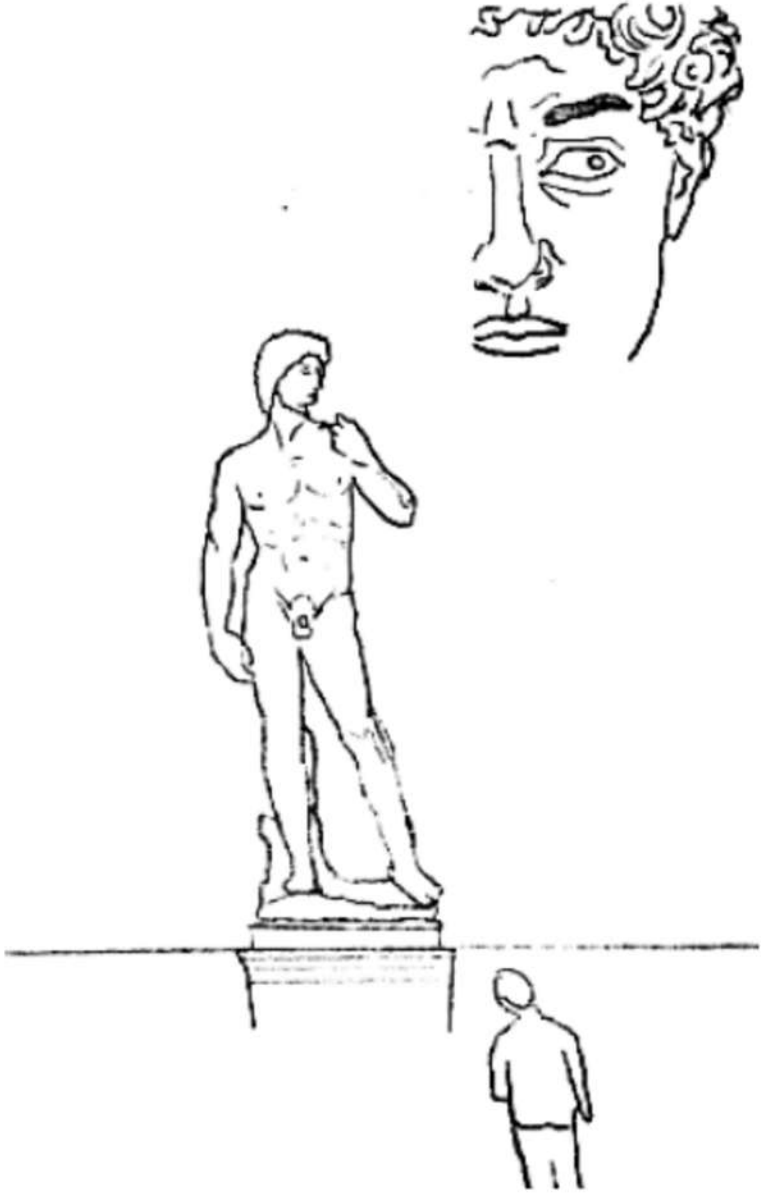

PORTAFOLIO

Manuel Emiliano Moreno Pérez
Urbanismo

01

DISTRIBUCIÓN DE TEMPERATURAS SUPERFICIALES (LST)

ATLAS METROPOLITANO DE BUENOS AIRES

Definición de las muestras: Se generaron 500 puntos aleatorios, cada uno representando 0.5 hectáreas y compuesto por 9 subpuntos de análisis.

Obtención del dato: Se realizó una revisión visual para cada muestra, seleccionando la imagen satelital más reciente y de mejor calidad, libre de nubes.

Clasificación de la cobertura: Cada subpunto fue categorizado en una de las siguientes clases: vegetación arbórea, vegetación no arbórea, construido, agua, cultivo o suelo desnudo.

Procesamiento estadístico: La base de datos resultante se analizó en Microsoft Excel, aplicando medidas de tendencia central, dispersión y percentiles. Finalmente, se elaboraron diagramas de cajas y bigotes para visualizar la relación entre cobertura y NDVI.

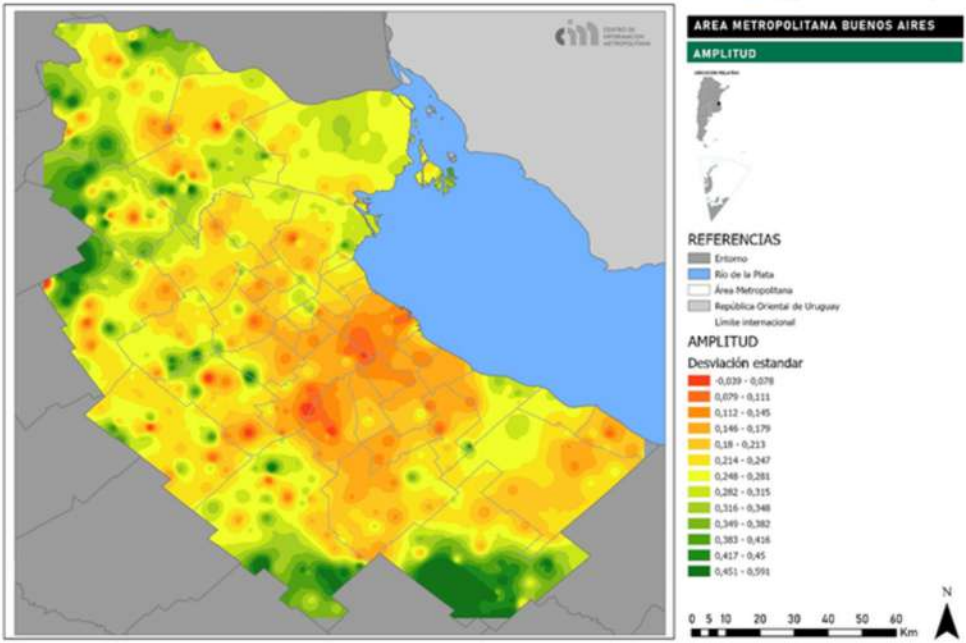

En el relevamiento realizado sobre 4.500 puntos analizados en el AMBA, se identificaron las siguientes coberturas:

- Vegetación no arbórea: 1.742 puntos
- Suelo desnudo: 999 puntos
- Vegetación arbórea: 976 puntos
- Área construida: 405 puntos
- Zonas de circulación: 277 puntos
- Cuerpos de agua: 101 puntos

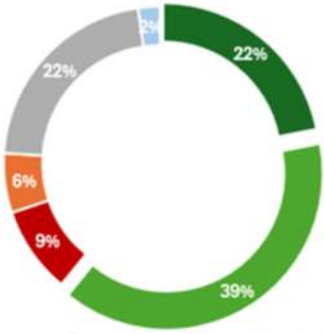

Elaboración propia. Datos generados a través del análisis y clasificación de coberturas del suelo mediante fotointerpretación satelital en el Área Metropolitana de Buenos Aires.

Este registro evidencia que la mayor cobertura corresponde a vegetación no arbórea, seguida por suelo desnudo y vegetación arbórea, lo que muestra un territorio aún heterogéneo, con **amplias extensiones sin cobertura construida, pero que no necesariamente representan espacios verdes** consolidados.

02

FRACCIONAMIENTO

LOS PÉTALOS DE CUAUTLA

PROPUESTA DE DISEÑO

AREA DEL POLIGONO: 78.2 ha
Nº VIVIENDAS: 2, 311 viviendas
o Lotes Unifamiliares: 1,471
o Lotes Multifamiliares: 70
(12 viviendas por lote = 840 viviendas)
POBLACIÓN TOTAL: 9,244 habitantes
(4 ocupantes por vivienda)
DENSIDAD DE POBLACIÓN:
118.21 hab/ha

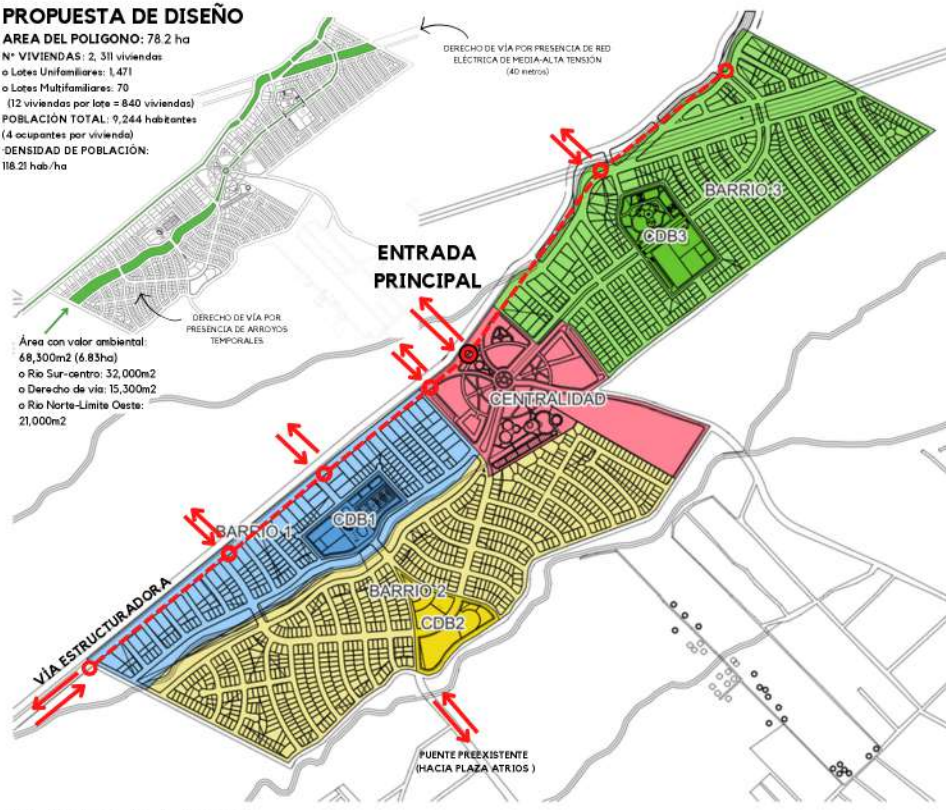

MANZANA TIPO

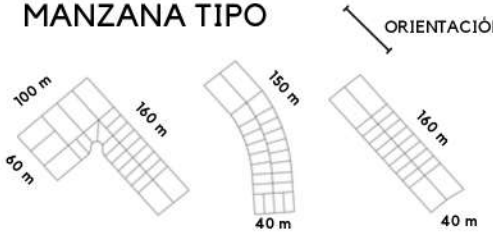

LOTE TIPO

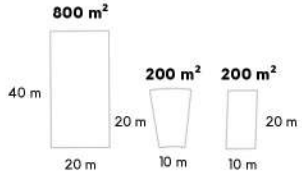

VIALIDAD COLINDANTE, DIVIDIDA EN UN SENTIDO A CADA LADO DEL RIO

VINCULACIÓN CON EL CONTEXTO

02

JERARQUÍA DE VIALIDADES

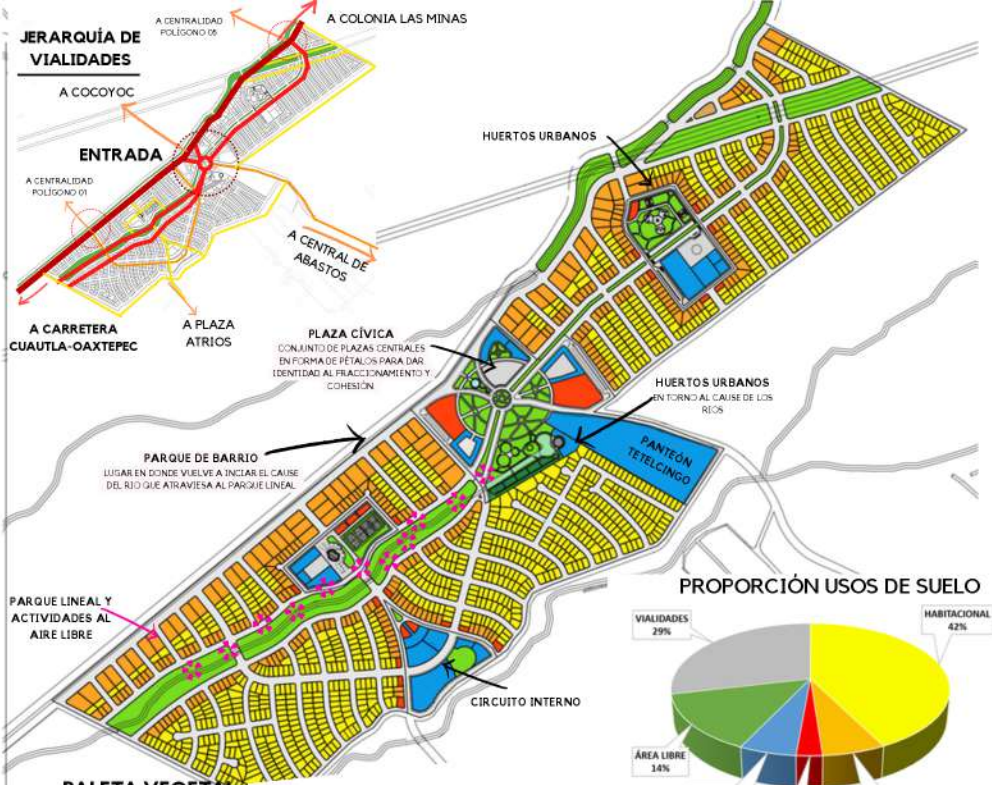

PROPORCIÓN USOS DE SUELO

PALETA VEGETAL

Encino

Ebano

antigonon leptopus

Cedro

Roble Yucateco

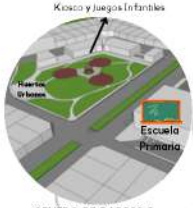

CENTRO DE BARRIO 3

Elemento Central: Huertos Urbanos y Juegos Infantiles

Unidad Deportiva

CENTRO DE BARRIO 1

Elemento Central: Teatro al Aire Libre

CENTRO DE BARRIO 2

Elemento Central: Deportivo y Juegos Infantiles

03

Ejes Vivos

Integración Urbana y Patrimonial en San Martín de los Andes

San Martín de los Andes es un **nodo turístico** clave en la ecoregión de Bosques Patagónicos, al **sur de Neuquén**. Aunque destaca por su patrimonio natural y cultural, su estructura urbana enfrenta desafíos de expansión, conectividad y resiliencia.

SOPORTE BIOFÍSICO

CONCEPTO - ¿QÚE SE PRETENDE?

Crear un San Martín de los Andes articulado mediante sistemas de conexión transversal que conecten las centralidades, vinculen y refuercen la integración espacial, social y ecológica de la ciudad.

OBJETIVOS

- Integrar la ciudad a través de ejes transversales
- Articular memoria, espacio y territorio
- Crear continuidad ecológica y urbana
- Conectar funcionalmente lo antiguo y lo emergente, reduciendo la dependencia del vehículo particular

ESTRATEGIAS

1. Consolidar cuatro ejes con identidad y funciones específicas: Cultural, turístico, deportivo e interdepartamental.

2. Generar un recorrido patrimonial desde el casco histórico hacia el nuevo Museo de la Defensa del Territorio Argentino

3. Conectar mediante un corredor ambiental sobre el riachuelo Cubúlco como espacio público lineal.

4. Impulsar un sistema vial jerarquizado, que combine movilidad vehicular, ciclovías y transporte público, mejorando la conexión longitudinal y transversal de la ciudad.

APOYO EN REDES

CONEXIONES TRANSVERSALES A LOS LÍMITES FÍSICO-NATURALES

UNIDAD COLECTIVA

ESPACIOS QUE FORTALECEN LA COHESIÓN SOCIAL Y CULTURAL

EQUILIBRIO VERDE

CORREDOR AMBIENTAL QUE EQUILIBRAN PAISAJE Y CIUDAD

CONECTIVIDAD VIAL

MOVILIDAD INTEGRAL PARA UNIR CENTRALIDADES

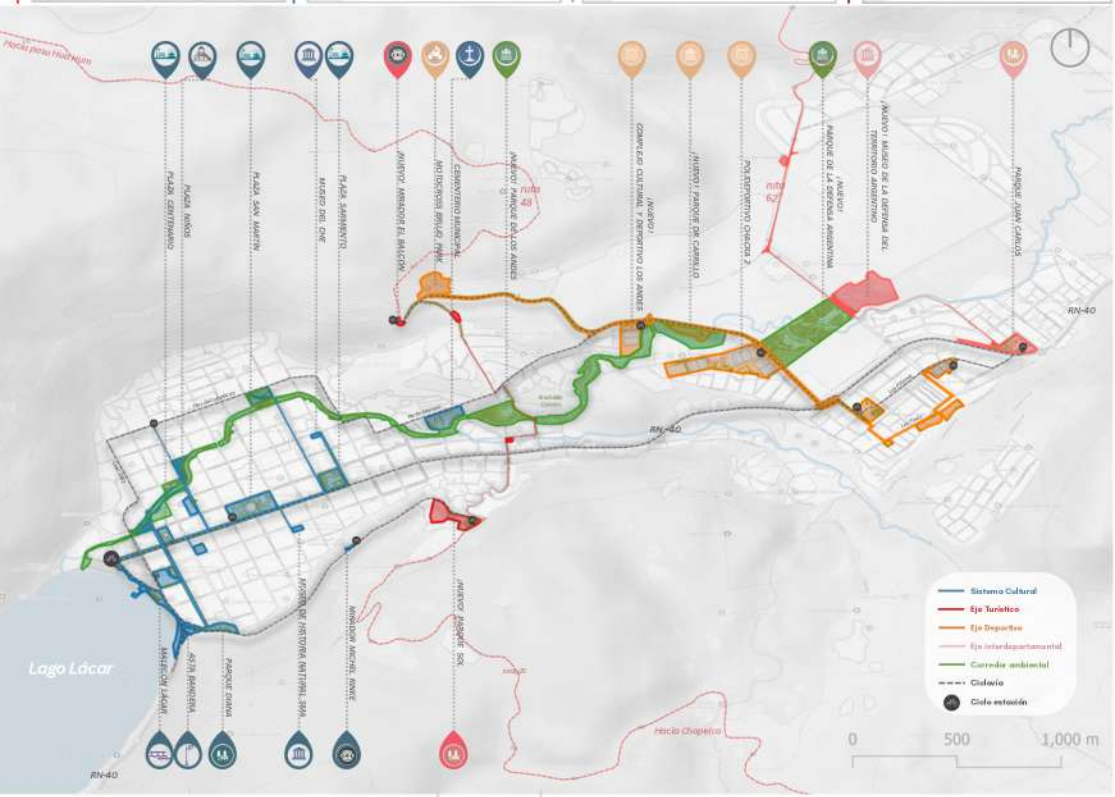

UBA, FADU.
UNIVERSIDAD DE BUENOS AIRES
Facultad de Arquitectura Diseño y Urbanismo

CÁTEDRA D'ANDREA
DISEÑO Y PLANIFICACIÓN DEL PASIAJE IV

ADJ: Victoria Gonzalez
JTP: Clara Miguens
DOC: D'Andrea

Manuel Emiliano, MORENO

2025

04

VULNERABILIDAD POR FACTORES DE BIENESTAR

ACAPULCO DE JUAREZ

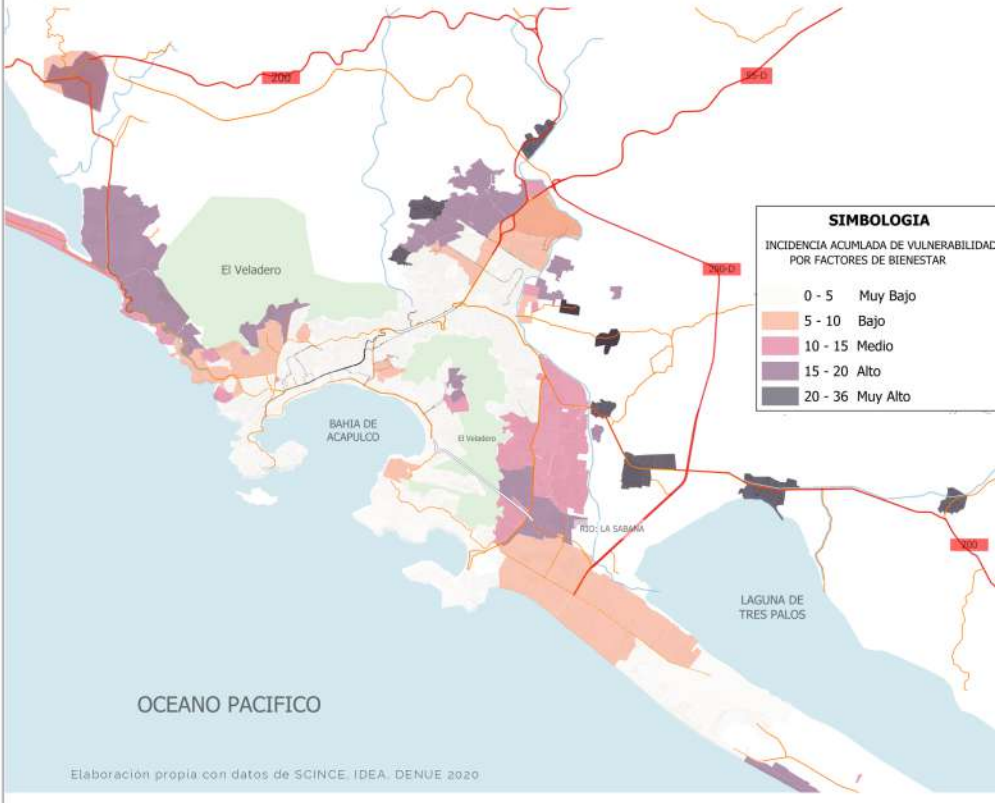

Calculo de la Matriz de Incidencia Acumulada (IA):

IA.vul = (V.inf + V.eqp + V.tp + V.Nse) * V. GMarg

donde:

IA.vul - Incidencia Acumulada de factores de vulnerabilidad por factores de bienestar en función de:

V.inf - Valor asociado a la presencia de infraestructura urbana
V.eqp - Valor asociado a la presencia de equipamiento.
V.tp - Valor asociado a la presencia de transporte público
V.Nse - Valor asociado a nivel socio-económico
V.GMarg - Valor asociado de acuerdo al grado de marginación

Elaboración propia.

Clasificación de Valores

INFRAESTRUCTURA	VALOR
CARECE DE AGUA	1
CARECE DE LUZ	1
CARECE DE DRENAJE	1

EQUIPAMIENTO & TRANSPORTE PUB.	VALOR
<100 M	0
101- 400 M	1
401-800 M	2
>800 M	3

SOCIO ECONÓMICO	VALOR
A-B	0
C	1
D	2
E	3

GRADO DE MARGINACIÓN	VALOR
BAJO	0
MEDIO	1
ALTO	2
MUY ALTO	3

VULNERABILIDAD POR FACTORES DE BIENESTAR

ACAPULCO DE JUAREZ

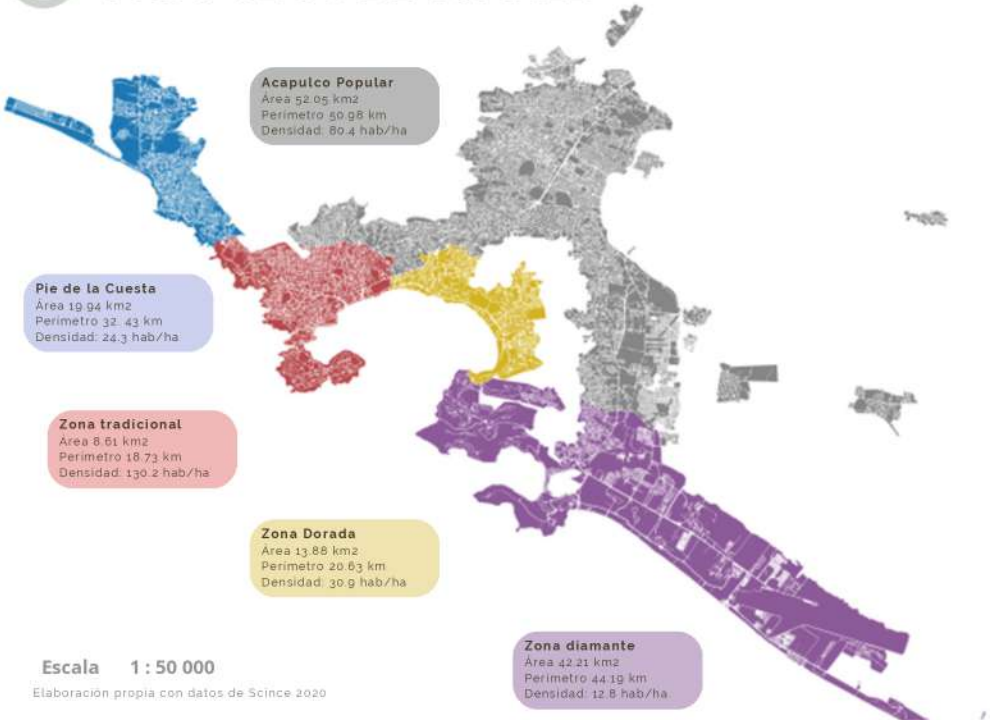

Elaboración propia con datos de Scince 2020

Consolidar **Polígonos de Actuación Concentrada (PAC)** en colonias distribuidas a lo largo de las vialidades San Lázaro, Blvd. Vicente Guerrero, Calle 14, Margarita Maza de Juárez (La Sabana, El Coloso y Renacimiento) y en Av. Fuerza Aérea Mexicana (Barra de Coyuca) esta propuesta incluye la **gestión y consolidación de la propiedad del suelo.**

¿CÓMO SE HARÁ? Consolidando colonias de actuación concentrada y de vivienda social **vulnerables por factores de bienestar** Para resolver el problema de la habilitación del suelo. Promoviendo la certeza jurídica y transparente.

A TRAVÉS DE : Gestión y consolidación del suelo (Agrupamiento parcelario) para el **desarrollo de proyectos urbanos integrales** de diferente índole que tendrán acción sobre polígonos con características de Lotes Baldíos que se aprovechan de las rentas generadas de la inversión publica y privadas.

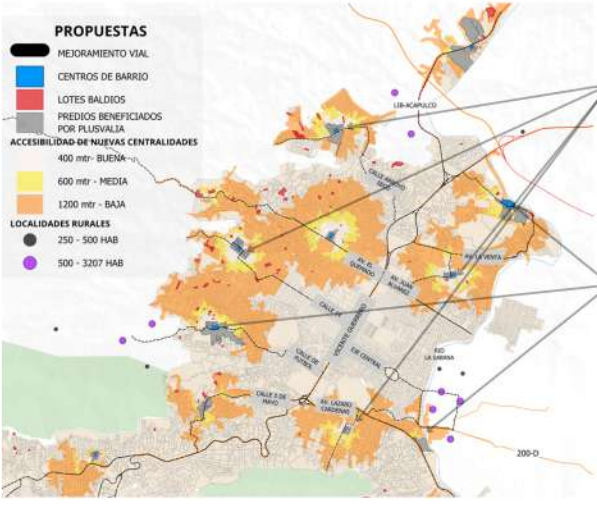

Mercado Publico
Área: 9 532 m2 /
Perímetro: 390 m

Parque Urbano
Área: 15 596 m2 /
Perímetro: 490 m

05

GRASSHOPPER

URBANO (PLUGGIN)

Topografía

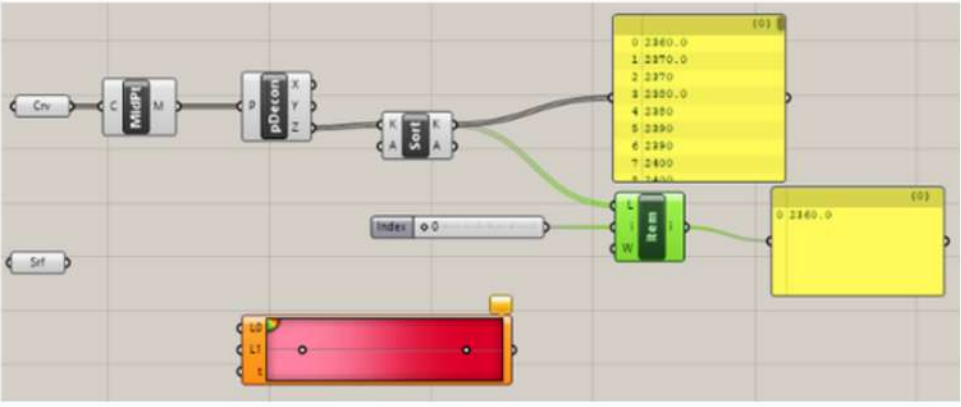

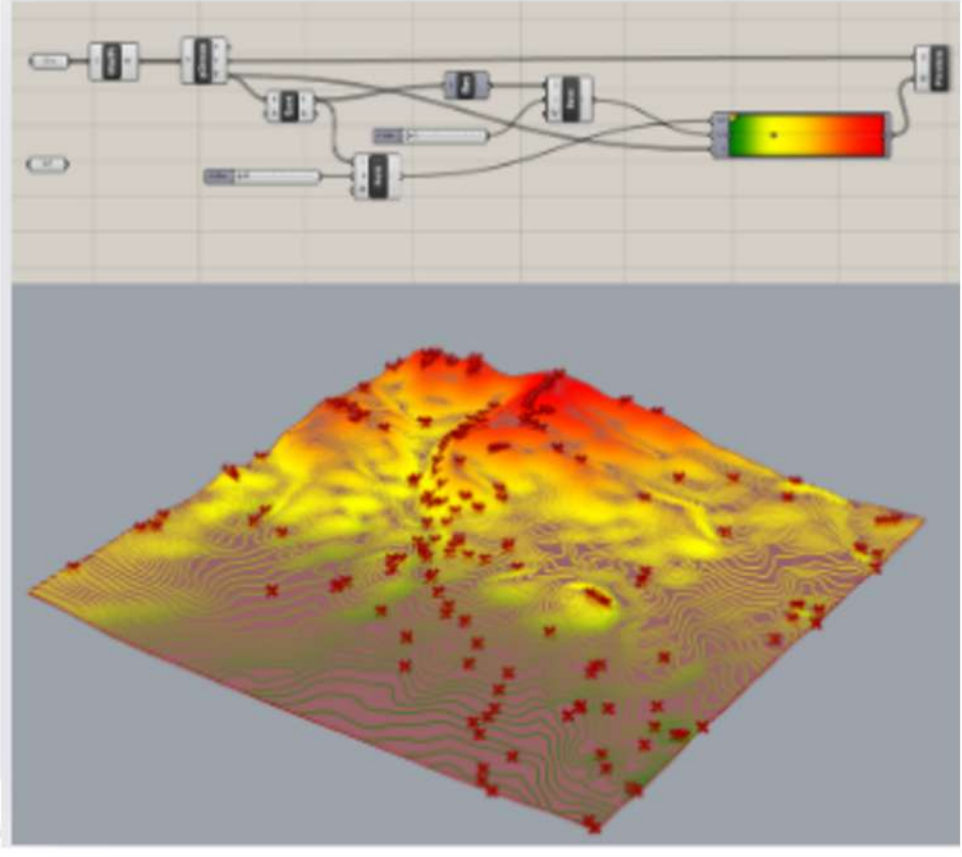

Rhinoceros
modeling tools for designers

06

LANDSAT

COMPOSICIÓN MULTIESPECTRAL DE IMÁGENES SATELITALES

Zona Metropolitana del Valle de México

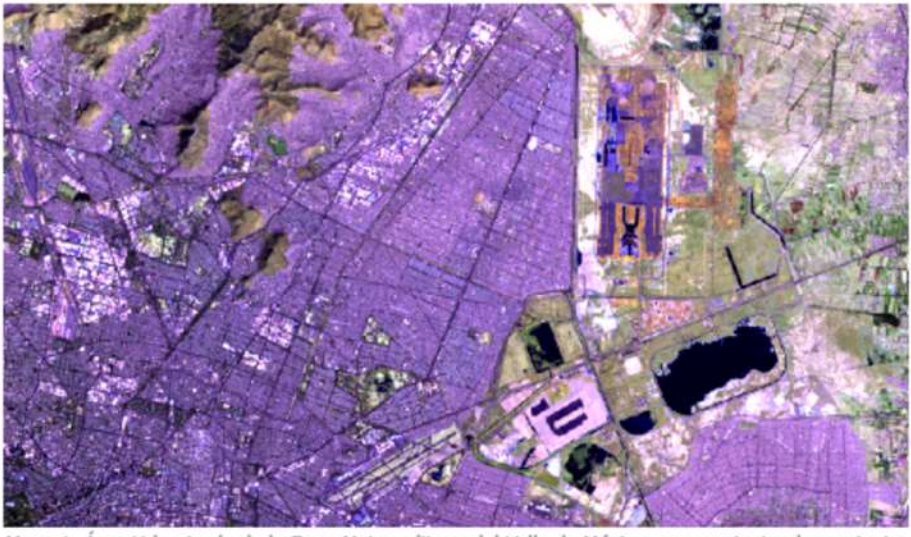

Mapa 1. Área Urbanizada de la Zona Metropolitana del Valle de México, acercamiento al nororiente de la Ciudad de México. Elaboración propia en QGis, con datos de EarthExplorer de USGS.

Morado = Área Urbana Naranja

Naranja = Humedad y cuerpos de agua estancados

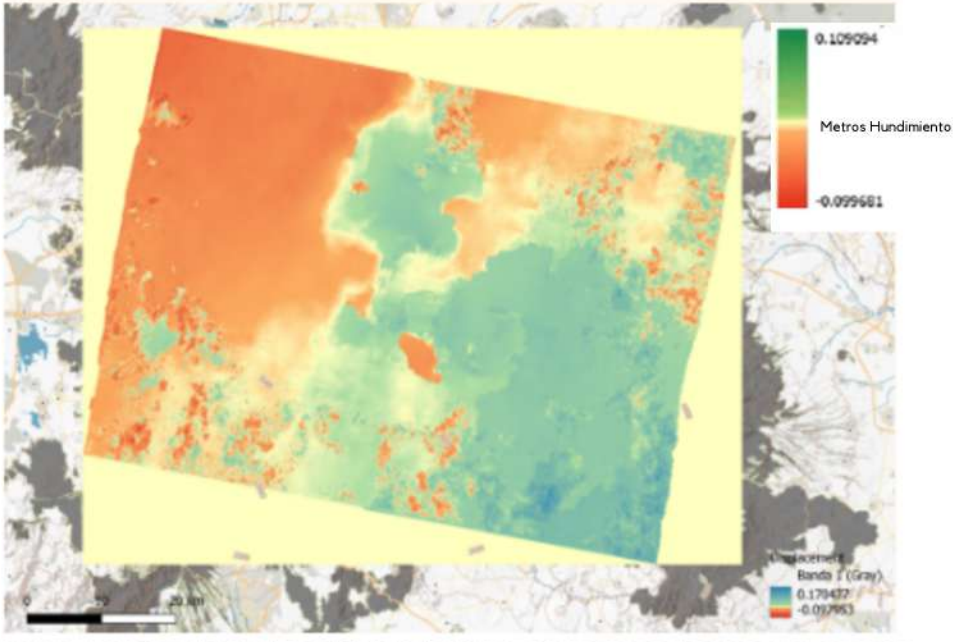

Producto Final. Zona Metropolitana del Valle de México, acercamiento a la zona centro, oriente y entro de la Ciudad de México. Elaboración propia con GraphBuilder : INSAR 2 y datos de Sistemas de Datos de Ciencias de la Tierra (ESDS) de la NASA

07

07

COATZACOALCOS

Proyecto Olmeca

RUTAS COATZACOALCOS INCORPORADAS:

La **movilidad intermodal** involucra varios medios de transporte, el tren, autobuses, taxis y bicidetas, mejora el acceso a servicios y empleos, atrae turismo y promueve la economía local. Además, se convierte en un punto de convergencia para múltiples proyectos de **desarrollo en la zona poniente de Coatzacoalcos,** aprovechando su conectividad con los sistemas de transporte.

CARRETERA COATZACOALCOS-MINITITLAN

TERMINAL INTERMODAL "OLMECA"

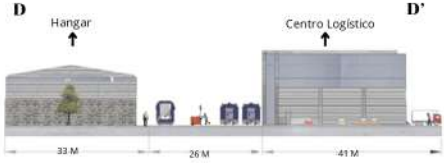

Regeneración Urbana

Proyecto Olmeca

CARRETERA A LAS BARRILLAS-COMPLEJO DEPORTIVO-CENTRO DE BARRIO

NUEVA SECCION DEL MALECON

PARQUE INUNDABLE-PARQUE LINEAL

Con el objetivo de fortalecer la conectividad entre diversos modos de transporte y mejorar el **acceso a servicios y empleos**, se plantea la necesidad de facilitar el traslado de bienes y mercancías, considerando tanto las áreas urbanas como las localidades rurales, para garantizar un acceso equitativo al transporte público para toda la población. Esta terminal se configura como un punto de convergencia para múltiples proyectos. Se propone la integración de distintos modos de transporte, como autobuses para traslados de corto y largo recorrido, una base de taxis para mejorar la movilidad interna, una ciclovía destinada a fomentar la movilidad activa, y la inclusión fundamental del tren con una estación ferroviaria. Esta estación contará con áreas dedicadas al ascenso y descenso de **pasajeros**, así como una sección exclusiva para la **carga y descarga de mercancías** con equipamiento.

08

JARDÍN DE NIÑOS

Jardín de Niños

Los Colorines

Ubicado en Av. Morelos #32 Popopark, Estado de México.

El Jardín de Niños "Colorines" se basa en la idea de crear un espacio educativo que fomente el aprendizaje, la creatividad y el desarrollo integral de los niños en un entorno seguro, estimulante y natural.

La arquitectura del jardín de niños integra elementos de color, formas orgánicas y materiales naturales para crear un ambiente acogedor, alegre y accesible para todos.

Manuel Emiliano Moreno Pérez

Ciudad de México
emisliano974@gmail.com
linkedin/in/manuel-emiliano-moreno-perez-b703b5345